APENDICE LETRA "C" NO. [illegible] VOL. [illegible]

SOL: SLRC P	SLRC PARQUE INDUSTRIAL 1, S. DE R.L. DE C.V.
CLAVE CATASTRAL:	6700 10 008 042
LOTE DE ORIGEN:	POL 11 F/N P-A
LOTE(S) RESULTANTE:	====
SUPERFICIE SEGÚN DOCUMENTO DE PROPIEDAD:	15,575.777 m²
SUPERFICIE SEGÚN LEVANTAMIENTO:	15,575.777 m²
MANZANA: === TIPO DE TRÁMITE:	DESLINDE
FECHA DE EMISIÓN:	MARTES 5 DE SEPTIEMBRE DE 2023
VIGENCIA:	LUNES 4 DE MARZO DE 2024

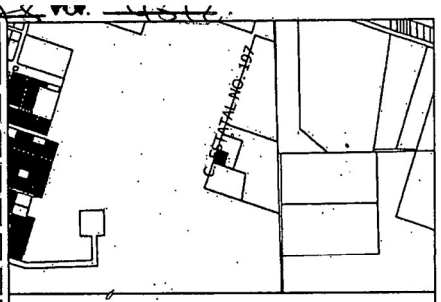

LOCALIZACION: CIUDAD DE SAN LUIS RIO COLORADO
MUNICIPIO DE SAN LUIS RIO COLORADO, SONORA

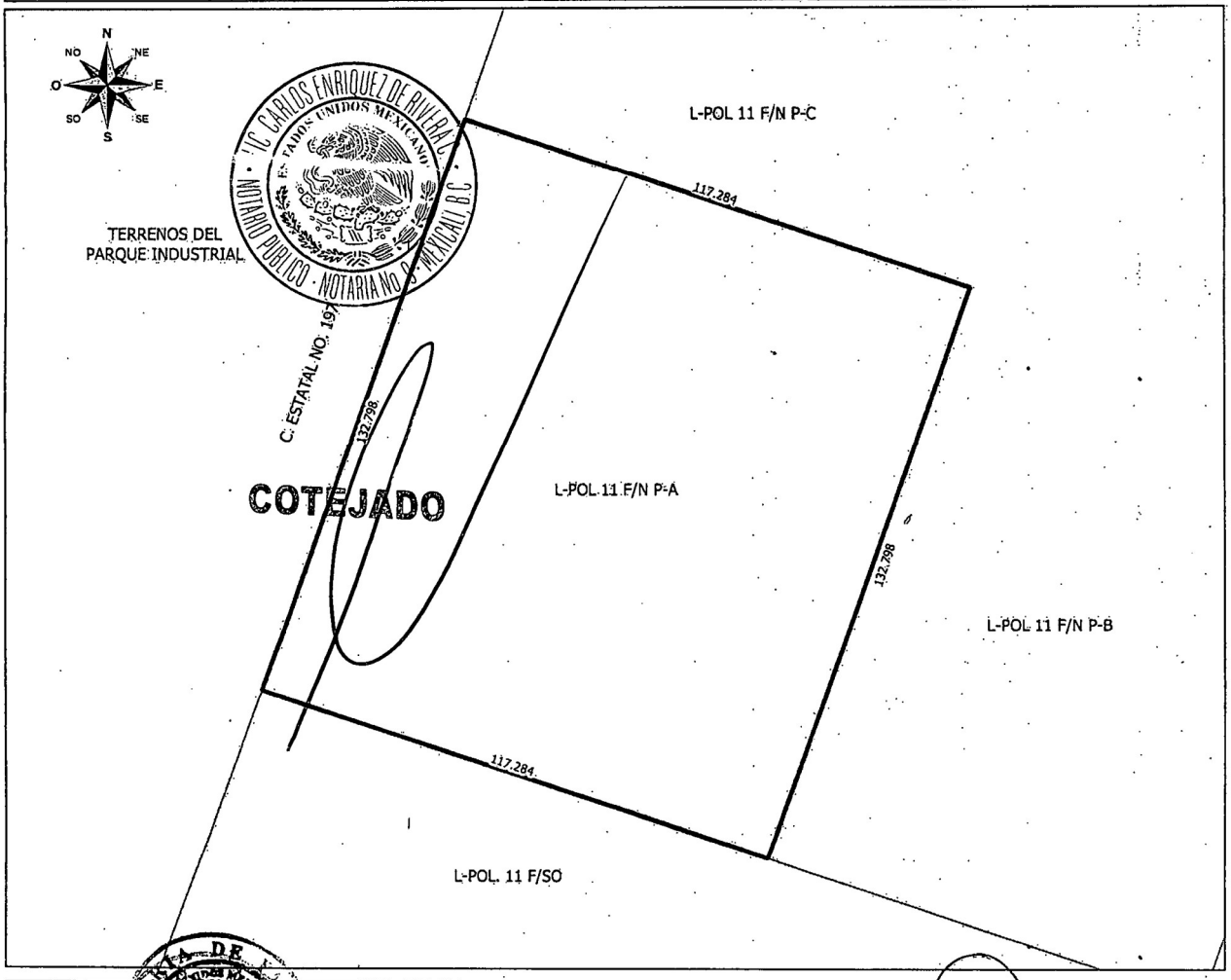

LIC. CARLOS ENRIQUEZ DE RIVERA C. ESTADOS UNIDOS MEXICANOS NOTARIO PUBLICO NOTARIA NO. 3 MEXICALI, B.C.

NOTAS:

ARQ. ENRIQUE MUNGUIA LOUSTAUNAU DIRECTOR DE CATASTRO	C. RAMÓN EMMANUEL VILLARREAL ACUÑA TOPÓGRAFO	C. JUAN CARLOS GUTIERREZ TORRES Vo. Bo. DEPTO. DE CARTOGRAFÍA Y TOPOGRAFÍA

DIRECCIÓN DE CATASTRO

SOLICITO:	**SLRC PARQUE INDUSTRIAL 1, S. DE R.L. DE C.V.**
CLAVE CATASTRAL:	**6700 10 008 041**
LOTE DE ORIGEN:	**POL 11 F/N P-B**
LOTE(S) RESULTANTE:	**====**
SUPERFICIE SEGÚN DOCUMENTO DE PROPIEDAD:	**48,174.20** m^2
SUPERFICIE SEGÚN LEVANTAMIENTO:	**48,174.20** m^2
MANZANA: **===**	TIPO DE TRÁMITE: **DESLINDE**
FECHA DE EMISIÓN:	**MARTES 5 DE SEPTIEMBRE DE 2023**
VIGENCIA:	**LUNES 4 DE MARZO DE 2024**

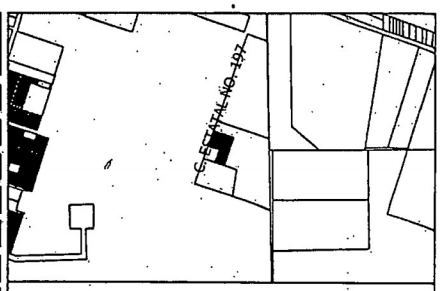

LOCALIZACIÓN: CIUDAD DE SAN LUIS RIO COLORADO
MUNICIPIO DE SAN LUIS RIO COLORADO, SONORA

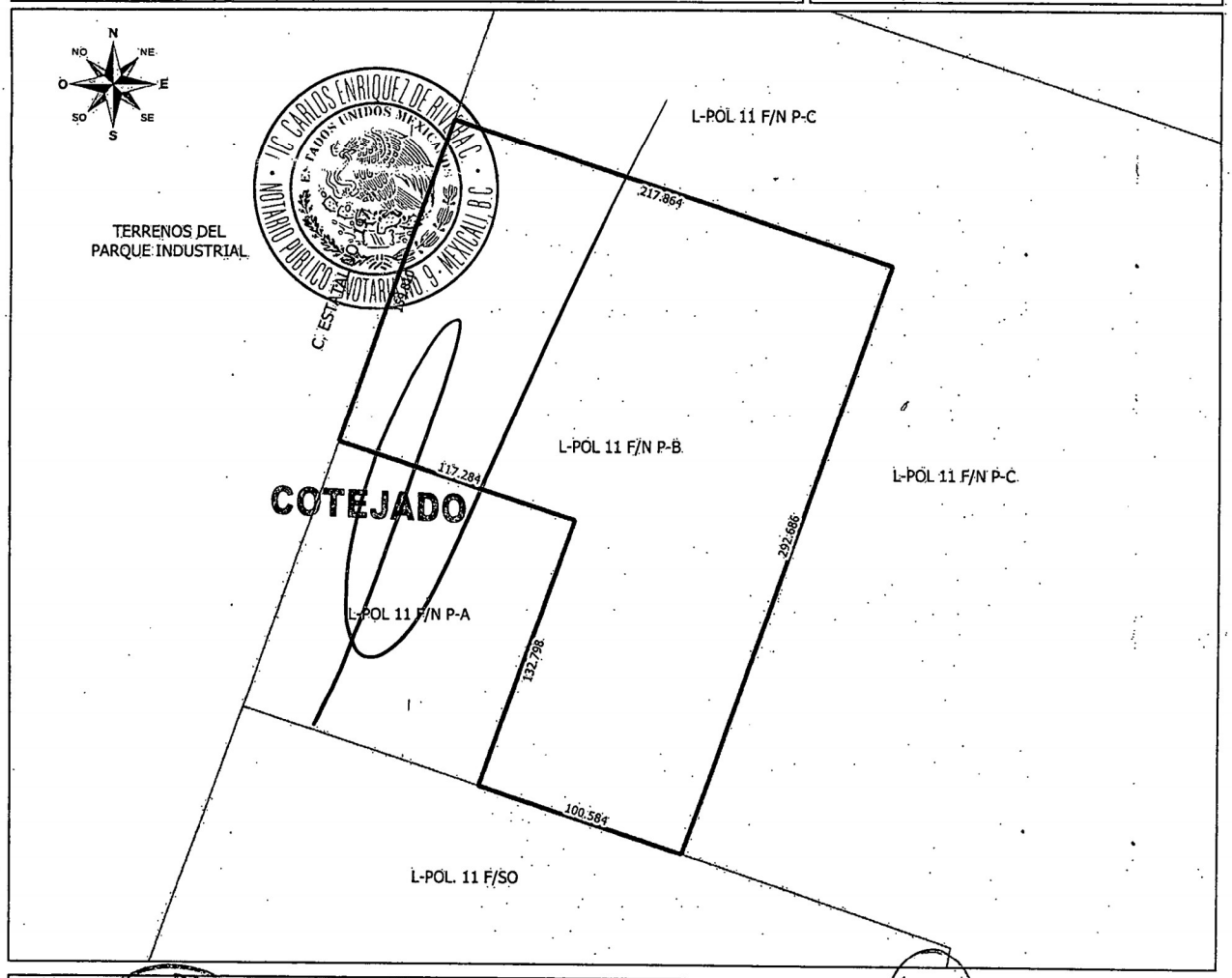

NOTAS:

ARQ. FEDERICO MUNGUIA GUSTAUNAU
DIRECTOR DE CATASTRO
San Luis Rio Colorado, Sonora

C. RAMÓN EMMANUEL VILLARREAL ACUÑA
TOPÓGRAFO

C. JUAN CARLOS GUTIÉRREZ TORRES
Vo. Bo. DEPTO. DE CARTOGRAFÍA Y TOPOGRAFÍA

DIRECCIÓN DE CATASTRO

SOLICITO:	SLRC PARQUE INDUSTRIAL 1, S. DE R.L. DE C.V.
CLAVE CATASTRAL:	6700 10 008 046
LOTE DE ORIGEN:	POL 11 F/N P-C
LOTE(S) RESULTANTE:	====
SUPERFICIE SEGÚN DOCUMENTO DE PROPIEDAD:	286,302.569 m²
SUPERFICIE SEGÚN LEVANTAMIENTO:	286,302.569 m²
MANZANA: ==	TIPO DE TRÁMITE: DESLINDE
FECHA DE EMISIÓN:	MARTES 5 DE SEPTIEMBRE DE 2023
VIGENCIA:	LUNES 4 DE MARZO DE 2024

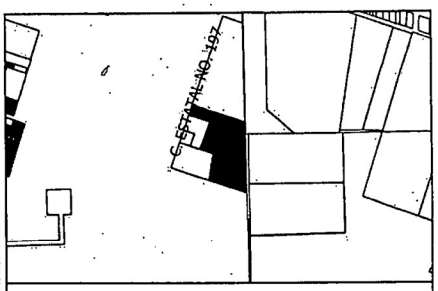

LOCALIZACIÓN: CIUDAD DE SAN LUIS RIO COLORADO
MUNICIPIO DE SAN LUIS RIO COLORADO, SONORA

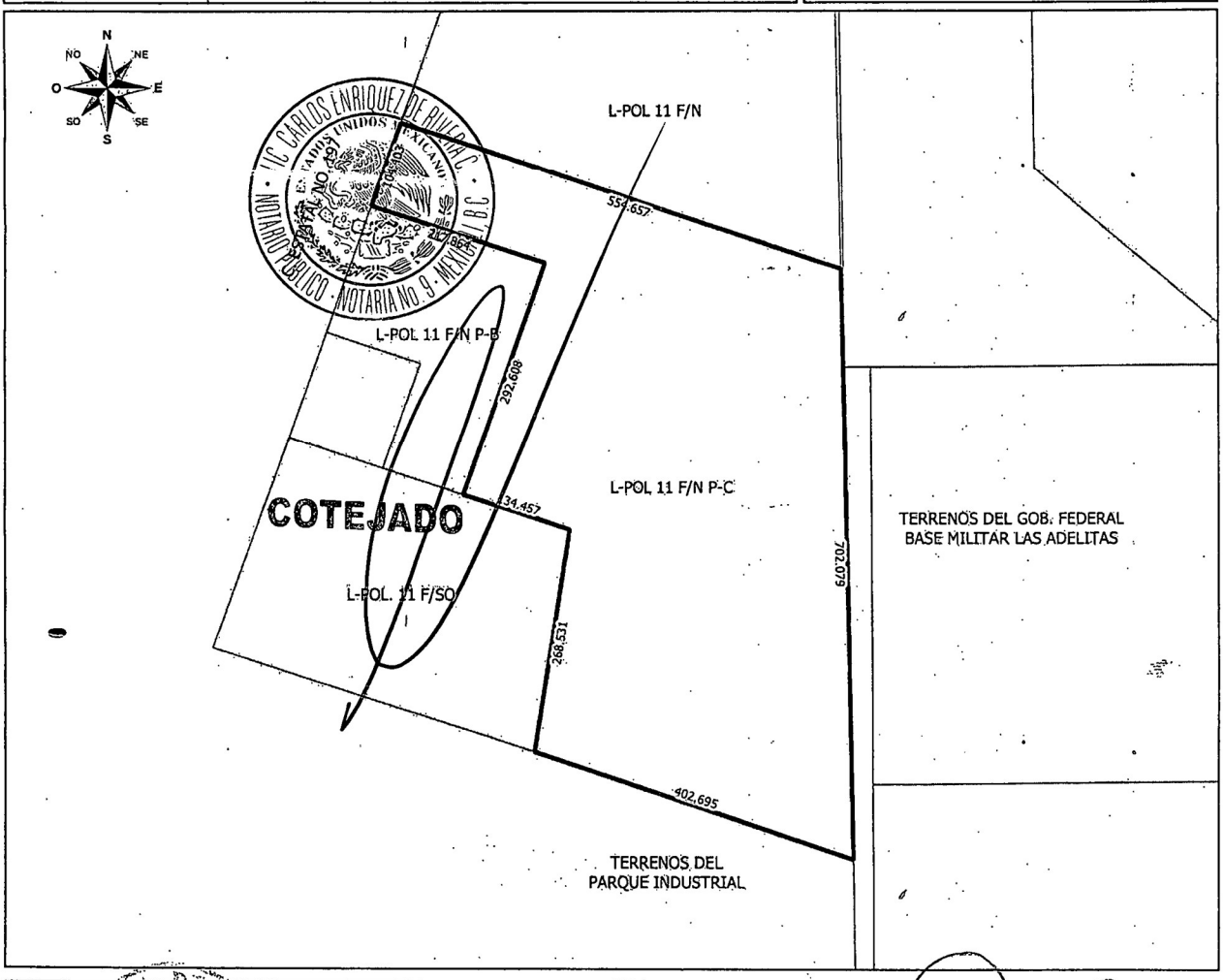

NOTAS:

ARQ. FEDERICO MUNGUIA LOUSTAUNAU DIRECTOR DE CATASTRO	C. RAMÓN EMMANUEL VILLARREAL ACUÑA TOPÓGRAFO	C. JUAN CARLOS GUTIÉRREZ TORRES Vo. Bo. DEPTO. DE CARTOGRAFÍA Y TOPOGRAFÍA

DIRECCIÓN DE CATASTRO