NOTA:

EL PRESENTE DESLINDE SE REALIZO EN BASE A:

*DESLINDE ANTERIOR DEL MISMO LOTE CERTIFICADO POR CATASTRO MUNICIPAL EL 29 DE OCTUBRE DE 1997.

*INSCRIPCION No.5136276 SECCION CIVIL DE FECHA 19 DE FEBRERO DE 1998 DEL REGISTRO PUBLICO DE LA PROPIEDAD Y DE COMERCIO REFERENTE A CONTRATO DE COMPRAVENTA, CON FOLIO REAL:172463.

EL PRESENTE TRABAJO SE ENCUENTRA LIGADO A LOS PUNTOS DE CONTROL CAT-58 ESTABLECIDO POR CATASTRO MUNICIPAL, C621 Y C622 ESTABLECIDOS POR CESPM EN COORDENADAS UTM DATUM WGS-84.

H. AYUNTAMIENTO DE MEXICALI
DESPACHADO
01 ABR 2017
DEPARTAMENTO DE CATASTRO
TOPOGRAFIA

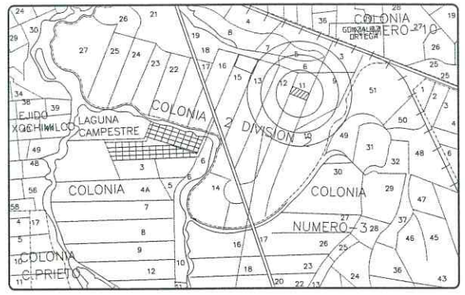

CROQUIS DE LOCALIZACION



(194.911) = DISTANCIA EN R.P.P. Y C.

194.910 = DISTANCIA ANALITICA

CUADRO DE CONSTRUCCION

LADO EST	LADO PV	RUMBO	DISTANCIA	V	COORDENADAS Y	COORDENADAS X
				1	3,606,182.6343	649,653.8447
1	2	S 63°05'33" E	191.398	2	3,606,096.0174	649,824.5214
2	3	S 24°35'44" W	48.141	3	3,606,052.2440	649,804.4845
3	4	S 22°43'12" W	55.819	4	3,606,000.7566	649,782.9256
4	5	N 63°05'33" W	194.910	5	3,606,088.9633	649,609.1164
5	1	N 25°31'29" E	103.802	1	3,606,182.6343	649,653.8447

SUPERFICIE = 20,000.000 M2.

DETALLE DE LIGA
FUERA DE ESCALA

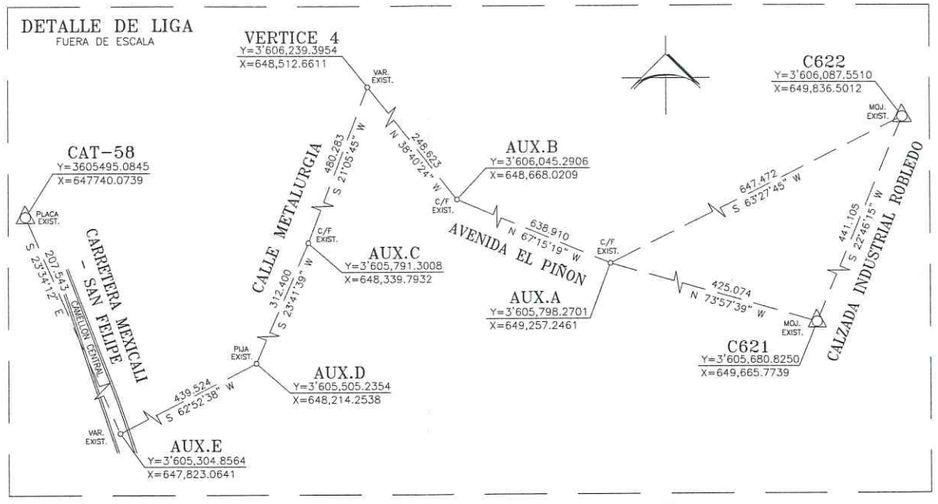

ACTA DE DESLINDE

CLAVE CATASTRAL	MANZANA	LOTE	SUPERFICIE
05-K0-501-102	S/M	11 FRACCION 1 PORCION 2	20,000.000 M2.

COLONIA, POBLADO O FRACCIONAMIENTO	DELEGACION (SI APLICA)	LUGAR
2 DIVISION 2	CERRO PRIETO	MEXICALI B.C.

PROPIETARIO O POSEEDOR: SPOT TECHNOLOGY MEXICO S.A. DE C.V.

SERVICIOS PUBLICOS: A ☒ L ☒ D ☒ B ☒ C ☒ P ☒ T ☒ G ☐ AL ☒ CV ☐

PREDIO	USO ACTUAL DEL SUELO	FECHA DE ELABORACION	PLANO	ESCALA	ACOTACION
CONSTRUIDO ○ BALDIO ◎	INDUSTRIAL	09 DE FEBRERO DE 2017	1/1	1: 1,200	METROS

EL DEPARTAMENTO DE CATASTRO MUNICIPAL DE MEXICALI

CERTIFICA

QUE EL PRESENTE DESLINDE CUMPLE CON LO ESTABLECIDO EN EL ARTICULO 44 DEL REGLAMENTO DEL CATASTRO INMOBILIARIO DEL MUNICIPIO DE MEXICALI Y ARTICULO XII DEL MANUAL TECNICO DE DESLINDES PARA EL MUNICIPIO DE MEXICALI, B. C. Y SALVO ERROR, OMISION O MODIFICACION, CORRESPONDEN A LOS DATOS QUE OBRAN EN ESTE DEPARTAMENTO DE CATASTRO BAJO CLAVE CATASTRAL INDICADA LOS CUALES FUERON VERIFICADOS Y REPLANTEADOS EN CAMPO POR EL PERITO FIRMANTE RESPONSABLE DE ESTOS TRABAJOS.

LOS DERECHOS FUERON PAGADOS CON EL RECIBO OFICIAL No. 81-D DE FECHA: 10/10/30/2017

EL C. COORDINADOR DEL AREA DE TOPOGRAFIA

ING. ADRIAN CERVANTES HUERTA

EL C. JEFE DEL DEPARTAMENTO DE CATASTRO

ARQ. KARLA CATALINA PEYNADO RAMIREZ

DEPTO. DE CATASTRO
ADMINISTRACION URBANA

☐ PROPIETARIO ☐ POSEEDOR ☐ REPRESENTANTE LEGAL

PERITO RESPONSABLE No. 36

ING. PABLO PEÑA RODRIGUEZ
CEDULA FEDERAL 714684 REGISTRO ESTATAL 4315/88
AV. ESPAÑA No. 2301 CONJ. URBANO ORIZABA
TEL.(686)557-40-00 E-MAIL servicios topgral@hotmail.com

REVISO

0/21010