LOTE ACTUAL

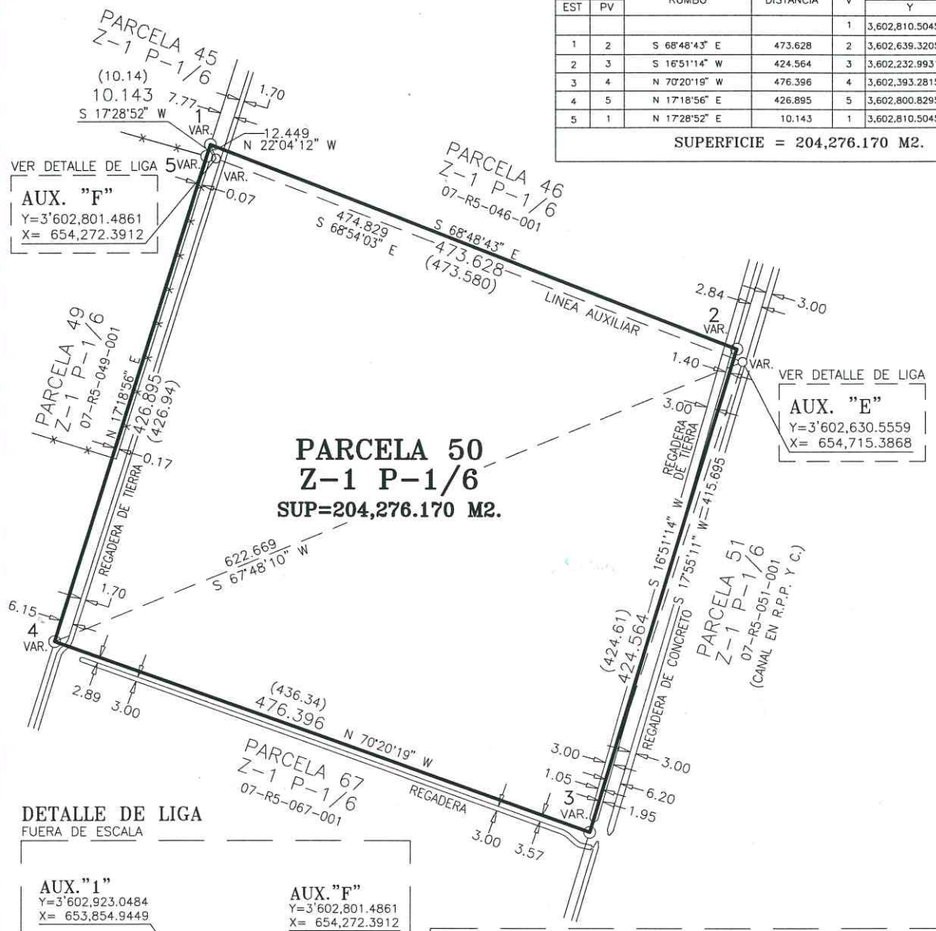

DETALLE DE LIGA

FUERA DE ESCALA

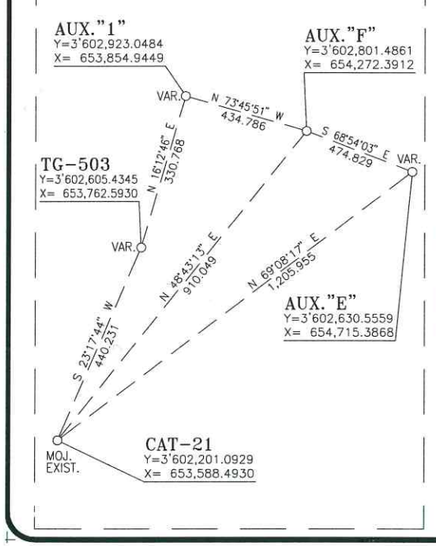

CUADRO DE CONSTRUCCION DEL POLIGONO GENERAL

LADO EST	LADO PV	RUMBO	DISTANCIA	V	COORDENADAS Y	COORDENADAS X
				1	3,602,810.5045	654,274.2403
1	2	S 68°48'43" E	473.628	2	3,602,639.3205	654,715.8507
2	3	S 16°51'14" W	424.564	3	3,602,232.9931	654,592.7555
3	4	N 70°20'19" W	476.396	4	3,602,393.2815	654,144.1343
4	5	N 17°18'56" E	426.895	5	3,602,800.8295	654,271.1933
5	1	N 17°28'52" E	10.143	1	3,602,810.5045	654,274.2403

SUPERFICIE = 204,276.170 M2.

CUADRO DE CONSTRUCCION DE LA PARCELA 50 Z-1 P-1/6 FRACCION 1

LADO EST	LADO PV	RUMBO	DISTANCIA	V	COORDENADAS Y	COORDENADAS X
				1	3,602,810.5045	654,274.2403
1	A	S 68°48'43" E	298.117	A	3,602,702.7556	654,552.2045
A	B	S 17°18'56" W	429.090	B	3,602,293.1121	654,424.4922
B	4	N 70°20'19" W	297.715	4	3,602,393.2815	654,144.1343
4	5	N 17°18'56" E	426.895	5	3,602,800.8295	654,271.1933
5	1	N 17°28'52" E	10.143	1	3,602,810.5045	654,274.2403

SUPERFICIE = 128,822.000 M2.

CUADRO DE CONSTRUCCION DE LA PARCELA 50 Z-1 P-1/6 FRACCION 2

LADO EST	LADO PV	RUMBO	DISTANCIA	V	COORDENADAS Y	COORDENADAS X
				A	3,602,702.7556	654,552.2045
A	2	S 68°48'43" E	175.511	2	3,602,639.3205	654,715.8507
2	D	S 16°51'14" W	12.034	D	3,602,627.8030	654,712.3615
D	C	N 68°48'43" W	175.608	C	3,602,691.2732	654,548.6248
C	A	N 17°18'56" E	12.027	A	3,602,702.7556	654,552.2045

SUPERFICIE = 2,106.714 M2.

SUBDIVISION PROPUESTA

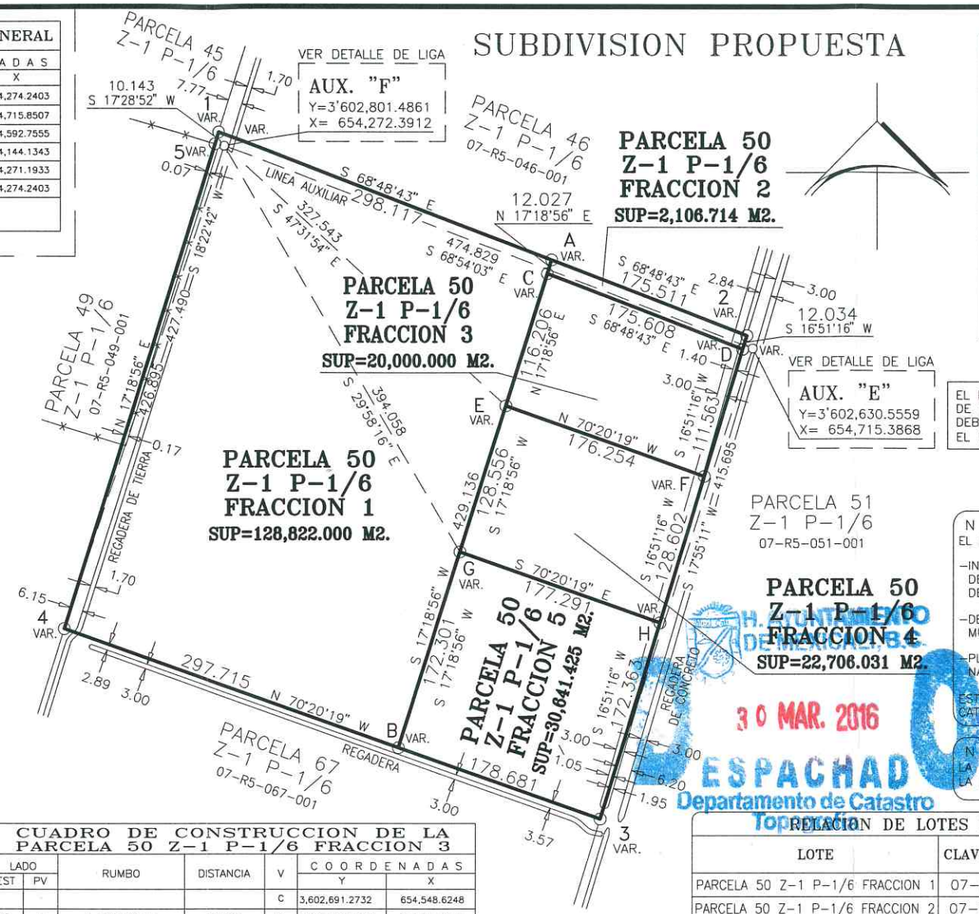

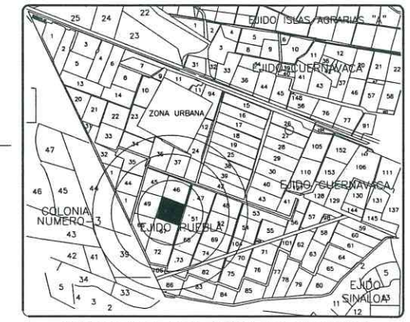

CROQUIS DE LOCALIZACION

EL PRESENTE DESLINDE CATASTRAL NO INCLUYE EL TRAZO DE FUTURAS VIALIDADES; PARA USO Y DESARROLLO DEL PREDIO DEBERAN SOLICITARSE LOS LINEAMIENTOS CORRESPONDIENTES EN EL DEPARTAMENTO DE INGENIERIA DE TRANSITO

(436.34) = DISTANCIA EN R.P.P. Y C.
476.343 = DISTANCIA ANALITICA

N O T A :
EL PRESENTE DESLINDE Y SUBDIVISION SE REALIZO EN BASE A:

-INSCRIPCION No.5750878 SECCION CIVIL ANTE EL R.P.P. Y C. DE FECHA 10 DE MARZO DEL 2016, REFERENTE A CONTRATO DE COMPRAVENTA. FOLIO REAL: 383857.

-DESLINDE ANTERIOR DEL MISMO LOTE CERTIFICADO POR CATASTRO MUNICIPAL DE FECHA 15 DE FEBRERO DE 2016.

-PLANO DE LOTIFICACION ELABORADO POR EL REGISTRO AGRARIO NACIONAL EN FEBRERO DE 1999.

ESTE TRABAJO SE ENCUENTRA LIGADO AL PUNTO DE CONTROL CAT-21 EN COORDENADAS UTM DATUM WGS-84.

N O T A :
LA PARCELA 50 Z-1 P-1/6 FRACCION 1 SE FUSIONARA CON LA PARCELA 49 Z-1 P-1/6.

H. AYUNTAMIENTO DE MEXICALI, B.C.
30 MAR. 2016
ESPACHADO
Departamento de Catastro
Topografía

CUADRO DE CONSTRUCCION DE LA PARCELA 50 Z-1 P-1/6 FRACCION 3

LADO EST	LADO PV	RUMBO	DISTANCIA	V	COORDENADAS Y	COORDENADAS X
				C	3,602,691.2732	654,548.6248
C	D	S 68°48'43" E	175.608	D	3,602,627.8030	654,712.3615
D	F	S 16°51'14" W	111.563	F	3,602,521.0315	654,680.0155
F	E	N 70°20'19" W	176.254	E	3,602,580.3338	654,514.0378
E	C	N 17°18'56" E	116.206	C	3,602,691.2732	654,548.6248

SUPERFICIE = 20,000.000 M2.

CUADRO DE CONSTRUCCION DE LA PARCELA 50 Z-1 P-1/6 FRACCION 4

LADO EST	LADO PV	RUMBO	DISTANCIA	V	COORDENADAS Y	COORDENADAS X
				E	3,602,580.3338	654,514.0378
E	F	S 70°20'19" E	176.254	F	3,602,521.0315	654,680.0155
F	H	S 16°51'14" W	128.602	H	3,602,397.9530	654,642.7294
H	G	N 70°20'19" W	177.291	G	3,602,457.6043	654,475.7751
G	E	N 17°18'56" E	128.556	E	3,602,580.3338	654,514.0378

SUPERFICIE = 22,706.031 M2.

CUADRO DE CONSTRUCCION DE LA PARCELA 50 Z-1 P-1/6 FRACCION 5

LADO EST	LADO PV	RUMBO	DISTANCIA	V	COORDENADAS Y	COORDENADAS X
				G	3,602,457.6043	654,475.7751
G	H	S 70°20'19" E	177.291	H	3,602,397.9530	654,642.7294
H	3	S 16°51'14" W	172.363	3	3,602,232.9931	654,592.7555
3	B	N 70°20'19" W	178.681	B	3,602,293.1121	654,424.4922
B	G	N 17°18'56" E	172.301	G	3,602,457.6043	654,475.7751

SUPERFICIE = 30,641.425 M2.

RELACION DE LOTES RESULTANTES DE LA SUBDIVISION

LOTE	CLAVE CATASTRAL	SUPERFICIE	USO DE SUELO
PARCELA 50 Z-1 P-1/6 FRACCION 1	07-R5-050-001	128,822.000 M2.	AGRICOLA
PARCELA 50 Z-1 P-1/6 FRACCION 2	07-R5-050-002	2,106.714 M2.	PASO DE SERVICIO
PARCELA 50 Z-1 P-1/6 FRACCION 3	07-R5-050-003	20,000.000 M2.	AGRICOLA
PARCELA 50 Z-1 P-1/6 FRACCION 4	07-R5-050-004	22,706.031 M2.	AGRICOLA
PARCELA 50 Z-1 P-1/6 FRACCION 5	07-R5-050-005	30,641.425 M2.	DONACION MUNICIPAL

ACTA DE DESLINDE Y SUBDIVISION

CLAVE CATASTRAL	MANZANA	LOTE	SUPERFICIE
07-R5-050-001	S/M	PARCELA 50 Z-1 P-1/6	204,276.170 M2.

COLONIA, POBLADO O FRACCIONAMIENTO	DELEGACION (SI APLICA)	LUGAR
EJIDO PUEBLA	GONZALEZ ORTEGA	MEXICALI B.C.

PROPIETARIO O POSEEDOR: CONSTRUCTORA BADEMI, S.A. DE C.V.

SERVICIOS PUBLICOS: A L D B C P T G AL CV

PREDIO	USO ACTUAL DEL SUELO	FECHA DE ELABORACION	PLANO	ESCALA	ACOTACION
CONSTRUIDO ○ BALDIO ◎	AGRICOLA	15 DE MARZO DE 2016	1/1	1:5,000	METROS

EL DEPARTAMENTO DE CATASTRO MUNICIPAL DE MEXICALI

CERTIFICA

QUE EL PRESENTE DESLINDE Y SUBDIVISION CUMPLE CON LO ESTABLECIDO EN EL ARTICULO 44 DEL REGLAMENTO DEL CATASTRO INMOBILIARIO DEL MUNICIPIO DE MEXICALI Y ARTICULO XII DEL MANUAL TECNICO DE DESLINDES PARA EL MUNICIPIO DE MEXICALI, B. C. Y SALVO ERROR, OMISION O MODIFICACION, CORRESPONDEN A LOS DATOS QUE OBRAN EN ESTE DEPARTAMENTO DE CATASTRO BAJO CLAVE CATASTRAL INDICADA, LOS CUALES FUERON VERIFICADOS Y REPLANTEADOS EN CAMPO POR EL PERITO FIRMANTE RESPONSABLE DE ESTOS TRABAJOS.

LOS DERECHOS FUERON PAGADOS CON EL RECIBO OFICIAL No. 86
DE FECHA: 22/03/2016

EL C. COORDINADOR DEL AREA DE TOPOGRAFIA
ING. ADRIAN CERVANTES HUERTA

EL C. JEFE DEL DEPARTAMENTO DE CATASTRO
ARQ. LEOPOLDO REYES GONZALEZ

JEFE DE CATASTRO

☐ PROPIETARIO ☐ POSEEDOR ☐ REPRESENTANTE LEGAL

PERITO RESPONSABLE No. 36
ING. PABLO PEÑA RODRIGUEZ
CEDULA FEDERAL 714684 REGISTRO ESTATAL 4315/88
AV. ESPAÑA No. 2301 CONJ. URBANO ORIZABA
TEL.(686)557-40-00 E-MAIL serviciostopgral@hotmail.com

REVISO

P/20625